

Prontuario de información geográfica municipal de los Estados Unidos Mexicanos

Papalotla de Xicohténcatl, Tlaxcala
Clave geoestadística 29041

2009

Prontuario de información geográfica municipal de los Estados Unidos Mexicanos
Papalotla de Xicohténcatl, Tlaxcala

Ubicación geográfica

Coordenadas	Entre los paralelos 19° 08' y 19° 12' de latitud norte; los meridianos 98° 08' y 98°14' de longitud oeste; altitud entre 2 100 y 2 500 m.
Colindancias	Colinda al norte con los municipios de Santa Catarina Ayometla, Santa Cruz Quilehla, Acuamanala de Miguel Hidalgo y Mazatecochco de José María Morelos; al este con los municipios de Mazatecochco de José María Morelos, San Pablo del Monte y Tenancingo; al sur con el municipio Tenancingo y el estado de Puebla; al oeste con el estado de Puebla y los municipios de Xicohtzinco y Santa Catarina Ayometla.
Otros datos	Ocupa el 0.6% de la superficie del estado Cuenta con 8 localidades y una población total de 24 616 habitantes http://mapserver.inegi.org.mx/mgn2k/ ; 22 de octubre de 2009.

Fisiografía

Provincia	Eje Neovolcánico (100%)
Subprovincia	Lagos y Volcanes de Anáhuac (100%)
Sistema de topoformas	Sierra volcánica con estrato volcanes o estrato volcanes aislados (100%)

Clima

Rango de temperatura	14 – 16°C
Rango de precipitación	800 – 1 000 mm
Clima	Templado subhúmedo con lluvias en verano, de mayor humedad (85%) y Templado subhúmedo con lluvias en verano, de humedad media (15%)

Geología

Periodo	Cuaternario (32%)
Roca	Suelo: aluvial (32%)

Edafología

Suelo dominante	Luvisol (23%), Cambisol (5%) y Arenosol (4%)
-----------------	--

Hidrografía

Región hidrológica	Balsas (100%)
Cuenca	R. Atoyac (100%)
Subcuenca	R. Atoyac-San Martín Texmelucan (81%) y R. Zahuapan (19%)
Corrientes de agua	Intermitentes Perennes: Atoyac
Cuerpos de agua	No disponible

Uso del suelo y vegetación

Uso del suelo	Agricultura (30%) y zona urbana (68%)
Vegetación	Bosque (2%)

Uso potencial de la tierra

Agrícola	Para la agricultura mecanizada continua (32%) No apta para la agricultura (68%)
Pecuario	Para el establecimiento de praderas cultivadas con maquinaria agrícola (32%) No apta para uso pecuario (68%)

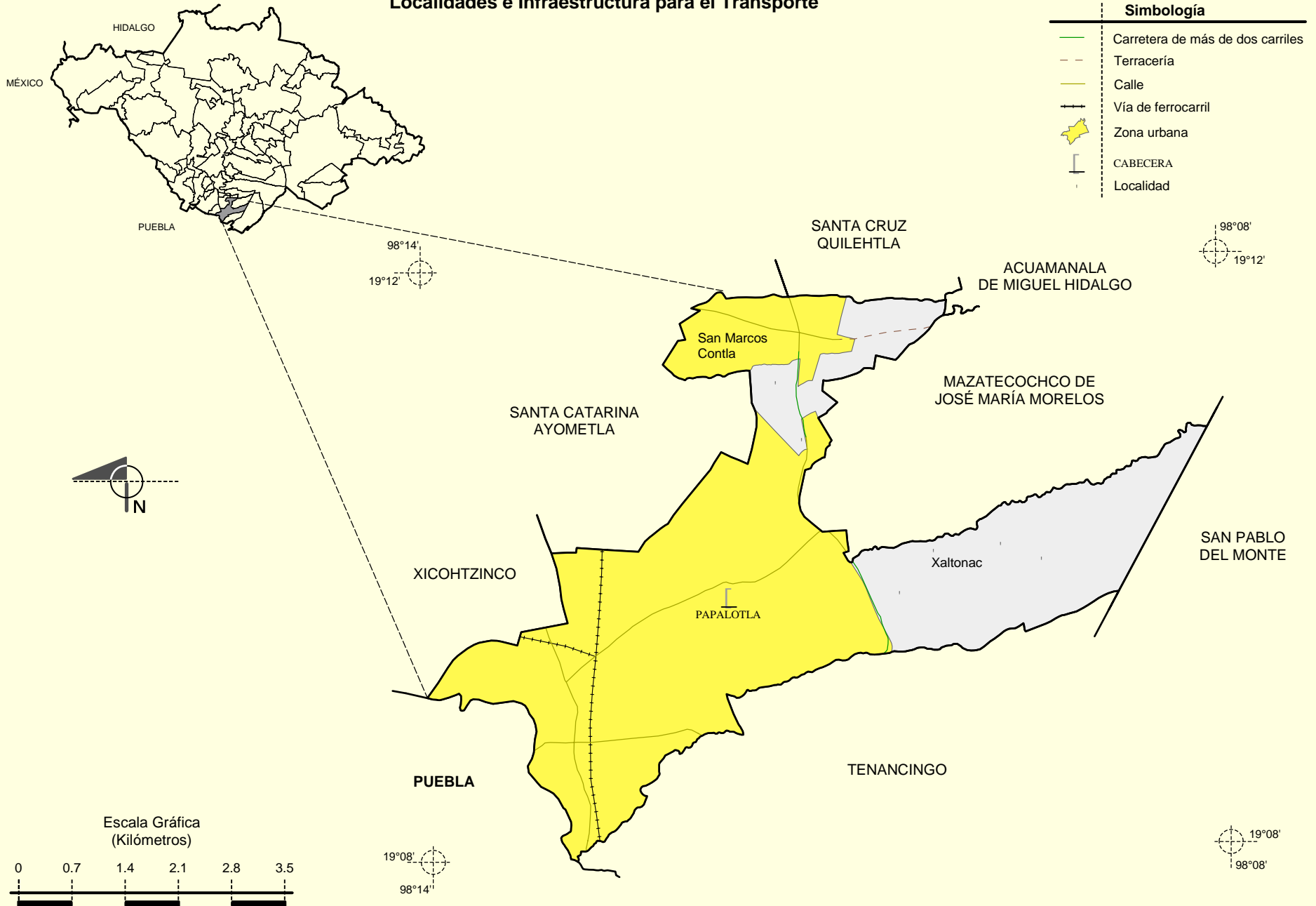
Prontuario de información geográfica municipal de los Estados Unidos Mexicanos

Papalotla de Xicohténcatl, Tlaxcala

Zona urbana

Las zonas urbanas están ubicadas sobre suelos del Cuaternario, en sierra volcánica con estrato volcanes o estrato volcanes aislados; sobre áreas donde originalmente había suelos denominados Luvisol y Cambisol; tienen clima templado subhúmedo con lluvias en verano de mayor humedad y templado subhúmedo con lluvias en verano de humedad media y están creciendo sobre terrenos ocupados previamente por agricultura.





Localidades e Infraestructura para el Transporte

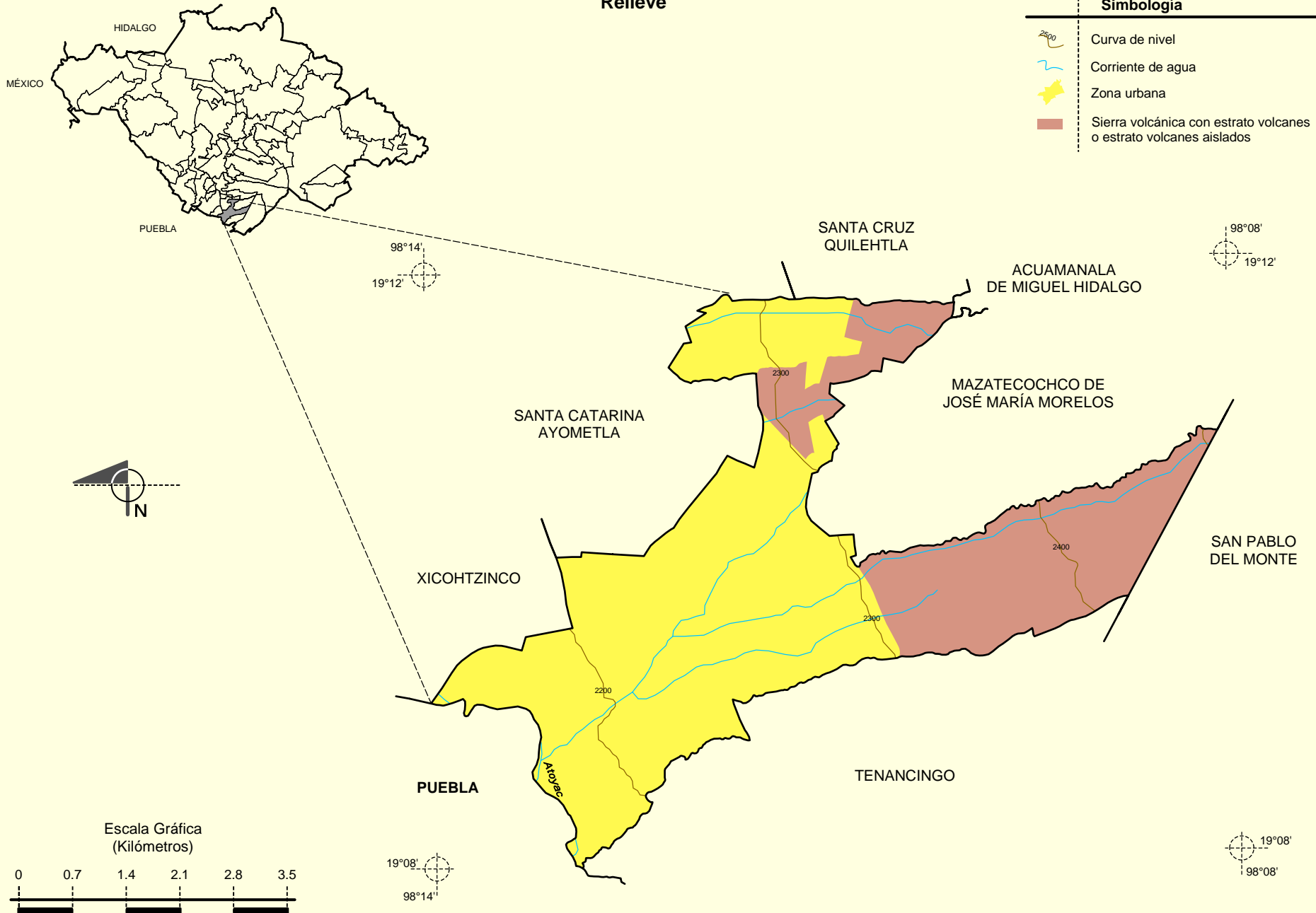


Prontuario de información geográfica municipal de los Estados Unidos Mexicanos
Papalotla de Xicohtécatl, Tlaxcala

Relieve

Simbología

-  Curva de nivel
-  Corriente de agua
-  Zona urbana
-  Sierra volcánica con estrato volcanes o estrato volcanes aislados

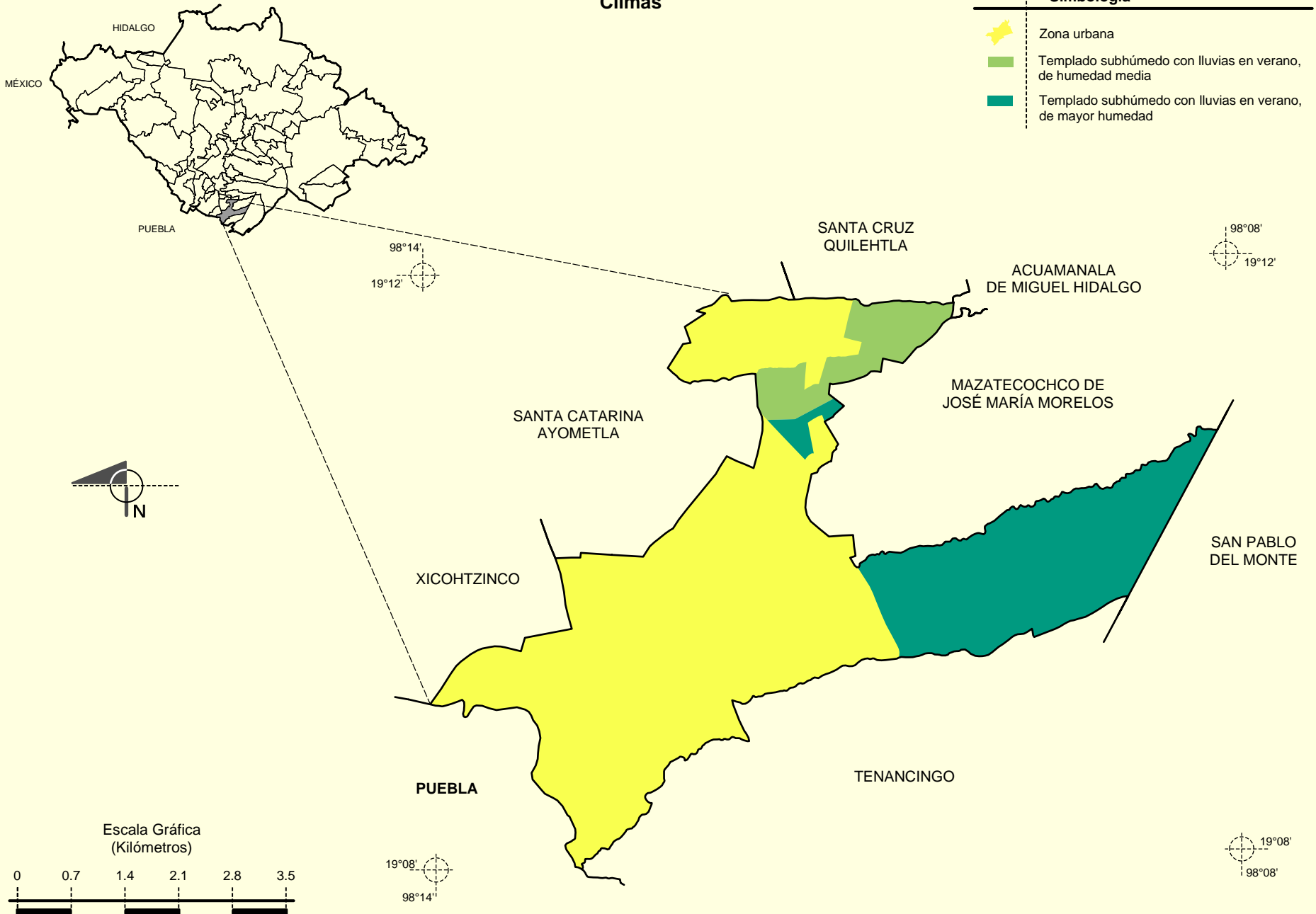


Fuente: INEGI. *Marco Geoestadístico Municipal 2005, versión 3.1.*
 INEGI. *Información Topográfica Digital Escala 1:250 000 serie III.*
 INEGI. *Continuo Nacional del Conjunto de Datos Geográficos de la Carta Fisiográfica 1:1 000 000, serie I.*
 INEGI-CONAGUA. 2007. *Mapa de la Red Hidrográfica Digital de México escala 1:250 000.* México.

**Prontuario de información geográfica municipal de los Estados Unidos Mexicanos
Papalotla de Xicohténcatl, Tlaxcala**

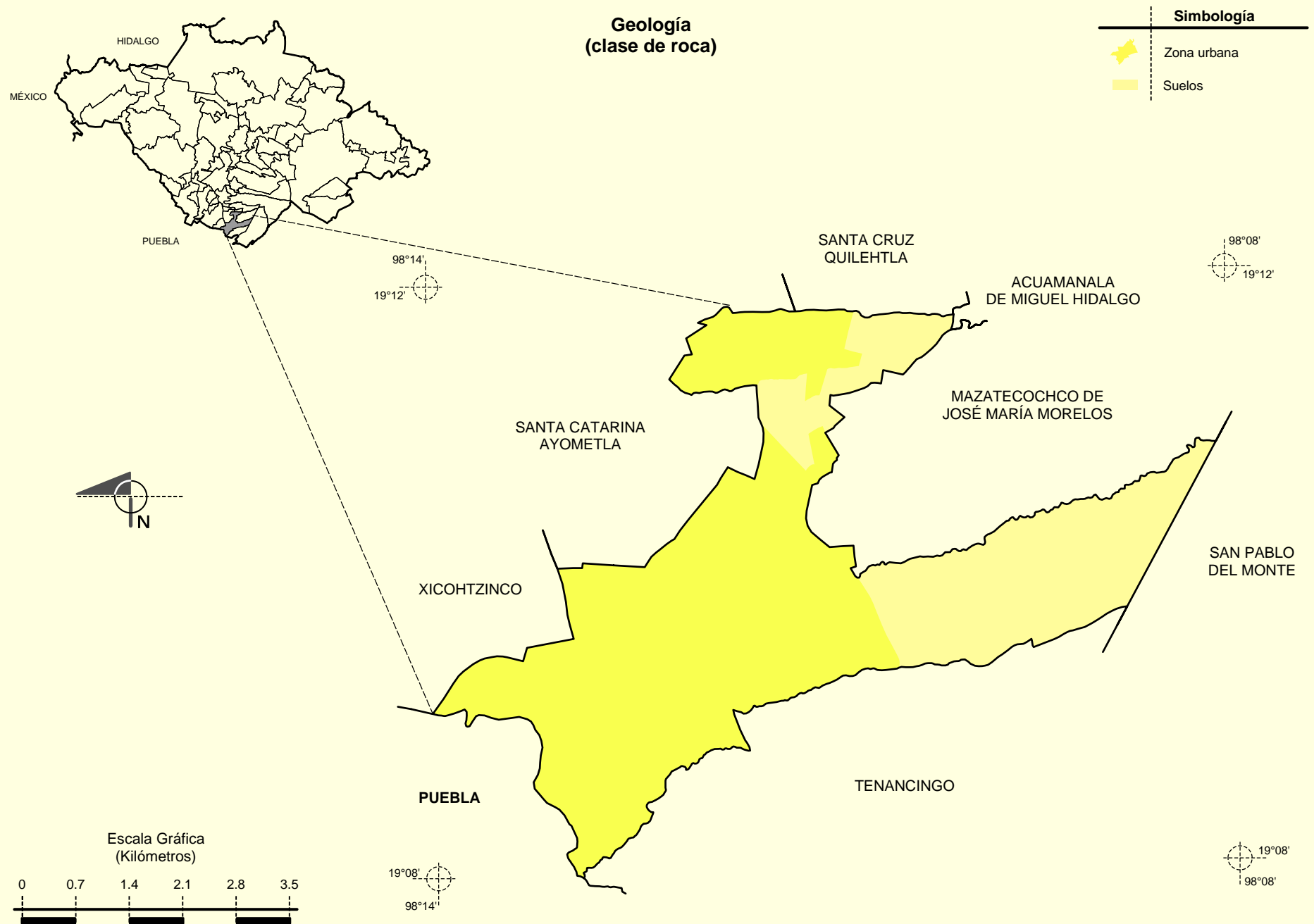
Climas

Simbología



Fuente: INEGI. Marco Geoestadístico Municipal 2005, versión 3.1.
INEGI. Continuo Nacional del Conjunto de Datos Geográficos de la Carta de Climas, serie I.





Prontuario de información geográfica municipal de los Estados Unidos Mexicanos
Papalotla de Xicohténcatl, Tlaxcala

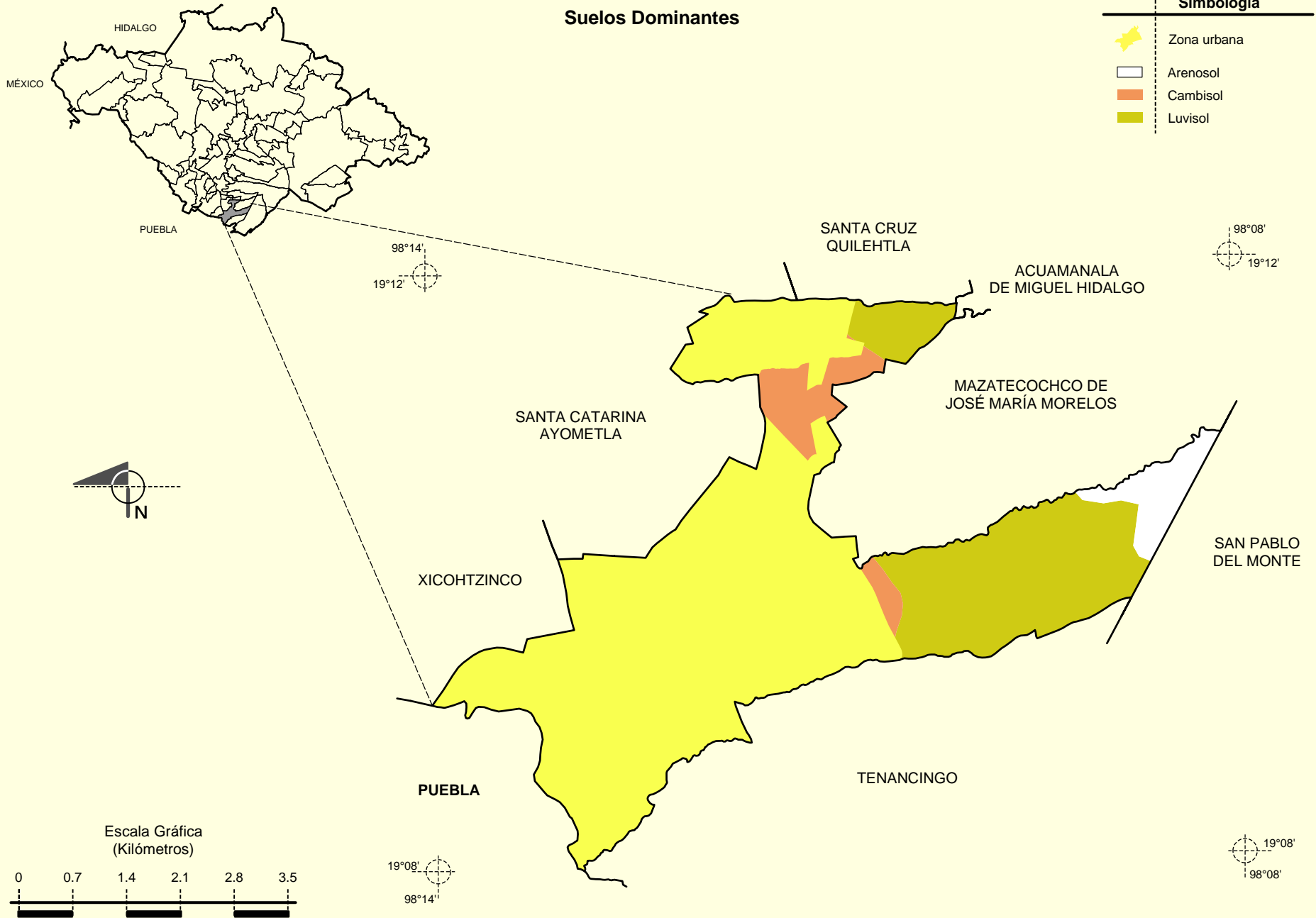


Prontuario de información geográfica municipal de los Estados Unidos Mexicanos
Papalotla de Xicohtécatl, Tlaxcala

Suelos Dominantes

Simbología




-  Zona urbana
-  Arenosol
-  Cambisol
-  Luvisol



Prontuario de información geográfica municipal de los Estados Unidos Mexicanos
Papalotla de Xicohténcatl, Tlaxcala

Uso del Suelo y Vegetación

Simbología

-  Zona urbana
-  Agricultura
-  Bosque

